Flächen

Brutto-Grundfläche (BGF)
Die Brutto-Grundfläche ist die Summe der Grundflächen aller Grundrissebenen eines Bauwerkes. Die BruttoGrundfläche ist in Netto-Grundfläche und Konstruktions-Grundfläche gegliedert.

Netto-Grundfläche (NGF)
Die Netto-Grundfläche ist die Summe der zwischen den aufgehenden Bauteilen befindlichen Bodenflächen (Fußbodenfläche) aller Grundrissebenen eines Bauwerkes. Die Netto-Grundfläche ist in Nutzfläche, Funktionsfläche und Verkehrsfläche gegliedert. Durch demontierbare Teile, freistehende Rohre und Leitungen sowie Ausstattungsgegenstände (zB mobile Trennwände, Badewannen) wird die Netto-Grundfläche nicht verringert. Fußbodenflächen innerhalb aufgehender Bauteile wie bei Türen, Fenstern, Durchgängen, nischenartigen Vertiefungen in umschließenden Bauteilen zählen nicht zur NettoGrundfläche. Bei Bedarf sind diese Flächen gesondert auszuweisen. Ist eine Zuordnung dieser Flächen zur NettoGrundfläche beabsichtigt, sind deren Randbedingungen projektspezifisch festzulegen und diese Flächen von der Konstruktions-Grundfläche abzuziehen. Teile der Netto-Grundfläche, die nicht aufrecht begehbar sind (zB unter Dachschrägen, unter Treppenläufen), sind bei Bedarf getrennt auszuweisen.

Nutzfläche (NF)
Die Nutzfläche dient der Nutzung des Bauwerkes aufgrund seiner Zweckbestimmung. Die Nutzfläche ist im Bedarfsfall in Hauptnutzflächen (HNF) und Nebennutzflächen (NNF) zu unterteilen. Mangels Festlegung kann für die Zuordnung die DIN 277.2 (1987-06), Tab. 1 und 2, herangezogen werden.

Hauptnutzfläche (HNF)
Die Hauptnutzfläche ist die Summe jener Flächen, die dem Verwendungszweck des Bauwerks unmittelbar dienen wie zB Wohnen, Arbeiten, Pflegen, Bildung, Freizeit.

Nebennutzfläche (NNF)
Zu den Nebennutzflächen werden jene Flächen gezählt, die nicht unmittelbar dem Verwendungszweck des Bauwerks dienen wie zB Sanitärräume, Garderoben, Abstellräume, Müllsammelräume, unausgebaute Dachbodenräume, Schutzräume, Fahrzeugabstellflächen.

Funktionsfläche (FF)
Die Funktionsfläche dient der Unterbringung von allgemein benötigten haustechnischen Einrichtungen samt den gegebenenfalls für sie allein erforderlichen Verkehrsflächen. Dazu gehören zB Räume für Heizungs-, Versorgungs- und Entsorgungseinrichtungen, begehbare Installationsnischen, -schächte und -gänge sowie Aufzugstriebwerksräume. Weitere Zuordnungen können der DIN 277.2 (1987-06), Tab. 2, Pkt. 8 entnommen werden. Die Fläche des Aufzugschachtes wird dem Geschoß des untersten Halts des Aufzugs zugezählt.

Verkehrsfläche (VF)
Die Verkehrsfläche dient dem Zugang und dem Verlassen von Nutz- oder Funktionsflächen oder dem Verkehr zwischen diesen Flächen. Die Flächen von Fahrtreppen und Fahrsteigen sind Verkehrsflächen.

Konstruktions-Grundfläche (KGF)
Die Konstruktions-Grundfläche ist die Differenz zwischen Brutto- und Netto-Grundfläche.

Berechnung von Grundflächen
Alle Grundflächen, die eine Verbindung zwischen Geschoßen herstellen, werden jeweils zum oberen dazugezählt (zB Treppen, Rampen, Fahrtreppen). Konstruktionsflächen zwischen unterschiedlichen Grundflächen sind dem jeweils geschlosseneren Bereich zuzuordnen, zB

- Umfassungen zwischen Bereich a und Bereich b gehören zu den Grundflächen,
- Umfassungen zwischen Bereich b und Außenraum gehören zu den Grundflächen.

A 1 Geschoßbezogene Grundflächen

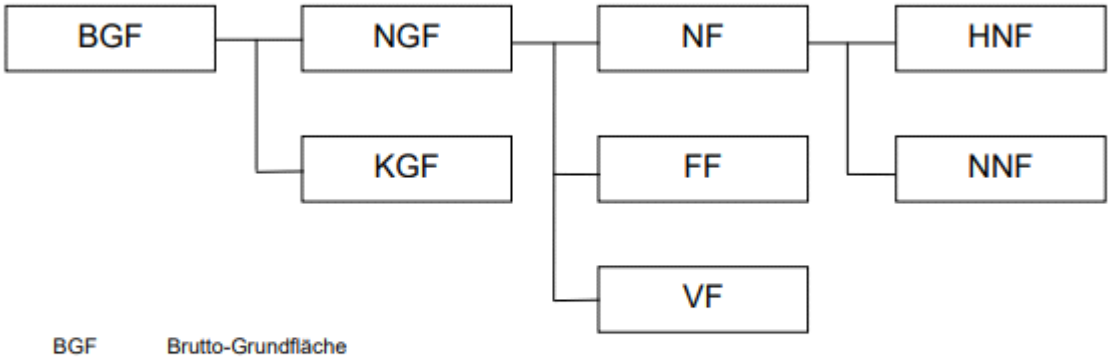

BGF	Brutto-Grundfläche
NGF	Netto-Grundfläche
NF	Nutzfläche
HNF	Hauptnutzfläche
KGF	Konstruktions-Grundfläche
FF	Funktionsfläche
NNF	Nebennutzfläche
VF	Verkehrsfläche

ÖN B 1800

Rauminhalte

Donnerstag, 24. Oktober 2019 09:02

Rauminhalte
(Brutto-Rauminhalt, Netto-Rauminhalt und Konstruktions-Rauminhalt)
Bereich a: überdeckt und allseitig in voller Höhe umschlossen (zB Innenräume).

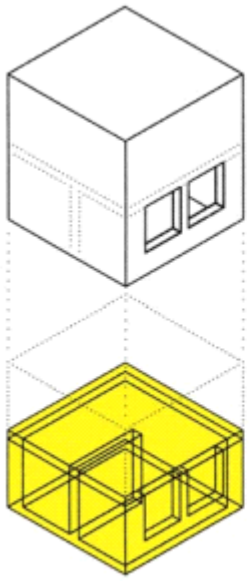

Brutto-Rauminhalt (BRIa)

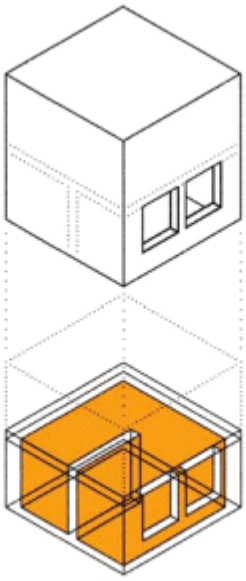

Netto-Rauminhalt (NRIa)

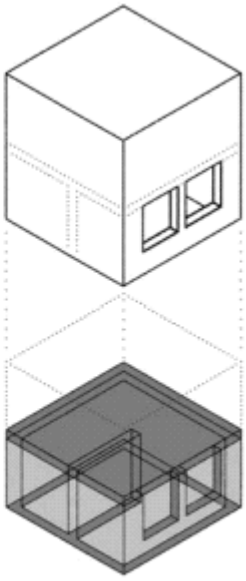

Konstruktions-Rauminhalt (KRIa)

Bereich b: überdeckt, jedoch nicht allseitig in voller Höhe umschlossen (zB überdeckte Außenräume).

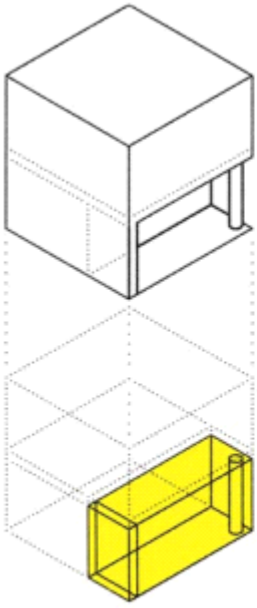

Brutto-Rauminhalt (BRIb)

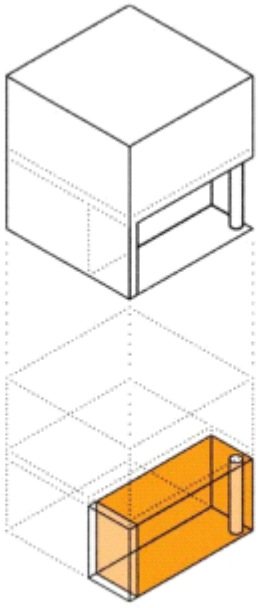

Netto-Rauminhalt (NRIb)

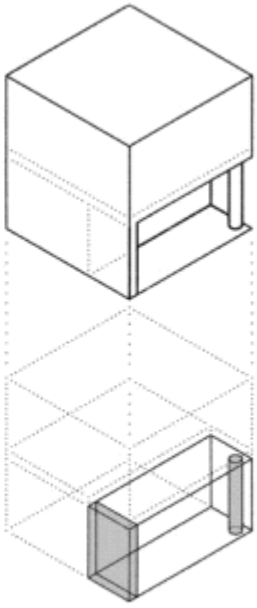

Konstruktions-Rauminhalt (KRIb)

Bereich c: nicht überdeckt, über Außendecken (zB nicht überdeckte Außenräume.

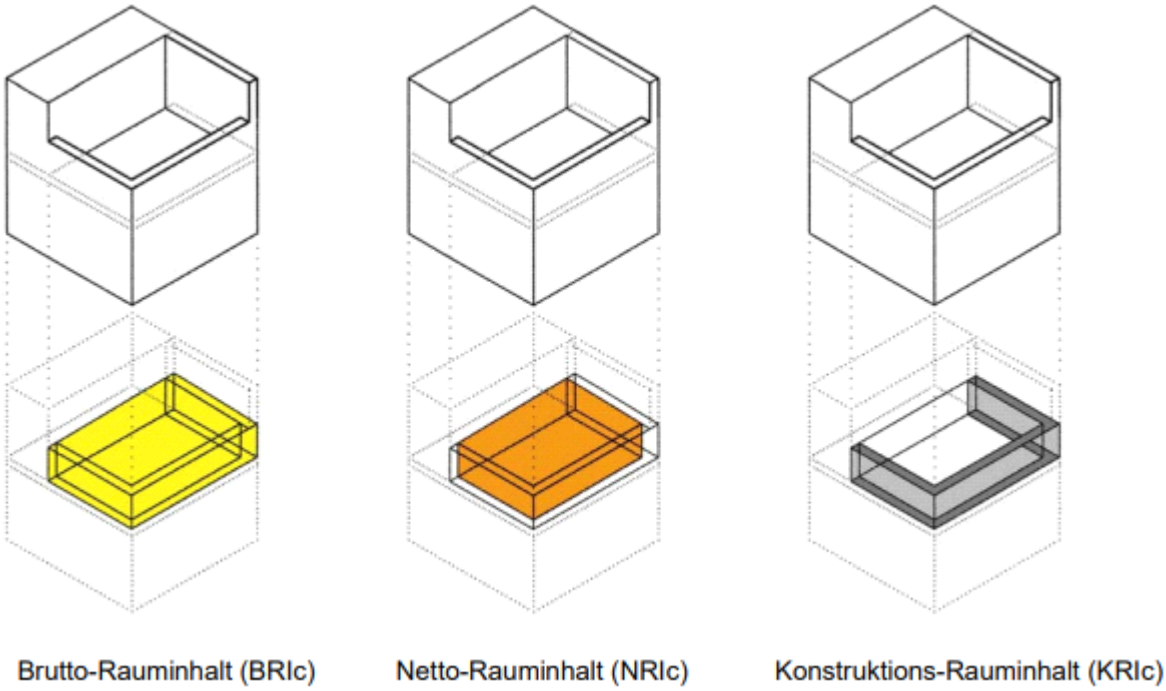

Weitere Unterteilungen können vorgenommen werden, wenn sich Bauwerksteile untereinander nach der Geometrie, Konstruktion, Ausstattung und Verwendung wesentlich unterscheiden (zB unausgebaute Dachräume, Garagen).

Brutto-Rauminhalt (BRI)
Der Brutto-Rauminhalt ist der Rauminhalt des Bauwerkes, der von den äußeren Begrenzungsflächen und nach unten von der Unterfläche der konstruktiven Bauwerkssohle umschlossen wird. Der Brutto-Rauminhalt ist in Netto-Rauminhalt und Konstruktions-Rauminhalt gegliedert.

Netto-Rauminhalt (NRI)
Der Netto-Rauminhalt ist der Rauminhalt aller Räume innerhalb der sie umschließenden Bauteile. Der Netto-Rauminhalt gliedert sich in Nettorauminhalt-Nutzfläche (NRI-NF), Nettorauminhalt-Funktionsfläche (NRIFF) und Nettorauminhalt-Verkehrsfläche (NRI-VF).

Konstruktions-Rauminhalt (KRI)
Der Konstruktions-Rauminhalt ist die Differenz zwischen Brutto- und Netto-Rauminhalt.

A 2 Rauminhalte

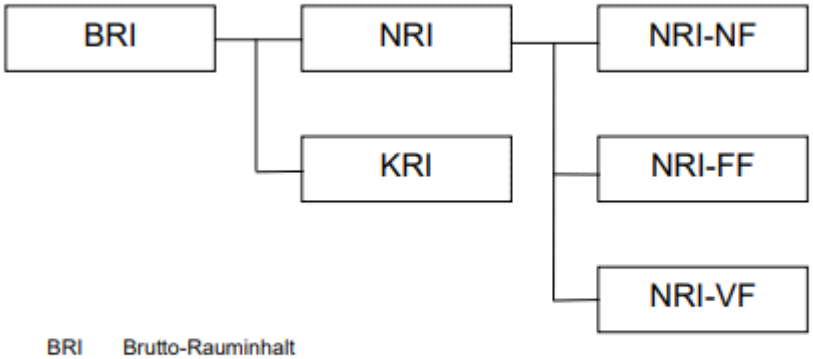

BRI Brutto-Rauminhalt
NRI Netto-Rauminhalt
NRI-NF Nettorauminhalt-Nutzfläche
KRI Konstruktions-Rauminhalt
NRI- FF Nettorauminhalt-Funktionsfläche
NRI-VF Nettorauminhalt-Verkehrsfläche

ÖN B 1800

Bauwerkshülle (Gebäudehülle)

Donnerstag, 24. Oktober 2019 11:03

Bauwerkshülle (Gebäudehülle) (HÜL)
Die Bauwerkshülle ist die Summe der äußeren Begrenzungsflächen des allseitig umschlossenen und überdeckten Bauwerkes bzw. Bauwerksteiles. Sie gliedert sich in die Außenwandfläche (AF), die Außengrundfläche (GF) und die Dachfläche (DF). Diese Flächen können in oberirdische und unterirdische unterteilt werden. Dabei können konstruktiv unterschiedliche Flächen gesondert erfasst werden (zB Glasflächen). Über die Bauwerkshülle hinausragende Bauteile sind nach Erfordernis gesondert zu erfassen. Sind Übergänge zwischen den einzelnen Teilflächen aufgrund der Ausformung der Bauwerkshülle fließend, insbesondere bei schrägen und gekrümmten Flächen, sind diese je nach Anforderung zB Funktion, Energie, Kosten den Flächen zuzuordnen.

Außenwandfläche (AF)
Die Außenwandfläche wird aus jenen Teilen der Bauwerkshülle, die nicht Außengrundfläche oder Dachfläche sind, gebildet.

Außengrundfläche (GF)
Die Außengrundfläche wird aus den untersten Begrenzungsflächen gebildet (Bauwerkssohle).

Dachfläche (DF)
Die Dachfläche wird aus den obersten Begrenzungsflächen gebildet.

A 3 Bauwerkshülle (Gebäudehülle)

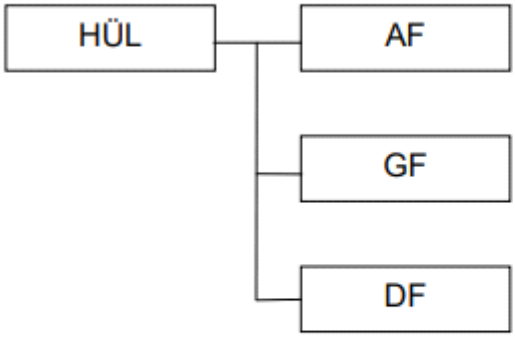

HÜL	Hüllfläche
AF	Außenwand- und Außendeckflächen
GF	Außengrundfläche
DF	Dachfläche

ÖN B 1800

Bruttogeschossfläche

Donnerstag, 24. Oktober 2019 11:11

ÖSTERREICH
Gemeinden können durch Verordnungen die Definition abändern.
Die Berechnung der Brutto-Grundfläche wird in der ÖNORM B-1800 festgelegt.

Bruttogeschoßfläche
die Fläche je Geschoß, die von den Außenwänden umschlossen wird, einschließlich der Außenwände;

Steiermärkisches Baugesetz
die Fläche je Geschoß, die von den Außenwänden umschlossen wird, einschließlich der Außenwände

<https://www.ris.bka.gv.at/GeltendeFassung.wxe?Abfrage=LrStmk&Gesetzesnummer=20000070>

Berechnungen

Donnerstag, 24. Oktober 2019 11:17

Bebauungsdichte
Verhältniszahl, die sich aus der Teilung der Bruttogeschoßfläche der Geschoße durch die zugehörige Bauplatzfläche ergibt

Bebauungsgrad
Verhältnis der bebauten Fläche zur Bauplatzfläche

Bebauungsweise
Verteilung der Baumassen auf dem Bauplatz in Bezug auf die Bauplatzgrenzen

a) offene Bebauungsweise:
   – allseits freistehende bauliche Anlagen oder
   – einseitig an die Grenzen angebaute bauliche Anlagen;

b) gekuppelte Bebauungsweise: an einer Grenze aneinandergebaute bauliche Anlagen;

c) geschlossene Bebauungsweise: an mindestens zwei Grenzen aneinandergebaute bauliche Anlagen;

<https://www.ris.bka.gv.at/GeltendeFassung.wxe?Abfrage=LrStmk&Gesetzesnummer=20000070>

Bauabgabe

Donnerstag, 24. Oktober 2019 11:22

(1) Anläßlich der Erteilung der Baubewilligung oder der Genehmigung der Baufreistellung ist dem Bauwerber von der Abgabenbehörde eine Bauabgabe vorzuschreiben. Für die Bauabgabe samt Nebengebühren haftet auf dem Grundstück, bei Superädifikaten oder Objekten nach dem Baurechtsgesetz auf den baulichen Anlagen, ein gesetzliches Pfandrecht. Wird von der Baubewilligung nicht Gebrauch gemacht, so ist die vorgeschriebene Bauabgabe bei späteren Baubewilligungen auf demselben Grundstück anzurechnen.

(2) Bei Zu- und Umbauten ist die Bauabgabe entsprechend der neugewonnenen Bruttogeschoßfläche zu berechnen.

(3) Die Bauabgabe errechnet sich aus dem Produkt von Einheitssatz je Quadratmeter und der Bruttogeschoßfläche. Dabei sind Erdgeschosse zur Gänze, die übrigen Geschosse (Tiefgaragengeschosse, Keller, Obergeschosse, Dachgeschosse u. dgl.) zur Hälfte zu berechnen.

(4) Der Einheitssatz beträgt EUR 8,72,–/m². Die Landesregierung kann durch Verordnung die Höhe des Einheitssatzes an die Entwicklung der Baukosten anpassen. Sie hat sich dabei an der Entwicklung des vom Österreichischen Statistischen Zentralamt veröffentlichten Baukostenindex zu orientieren.

(5) Die Bauabgabe ist eine ausschließliche Gemeindeabgabe im Sinne § 6 Abs. 1 Z 5 des Finanz-Verfassungsgesetzes 1948.

(6) Die Abgaben sind zur Finanzierung von folgenden Maßnahmen zweckgebunden:

1. Herstellung von Verkehrsflächen, Oberflächenentwässerungen und Straßenbeleuchtungen;
2. Übernahme von Grundstücken in das öffentliche Gut;
3. Errichtung und Gestaltung von öffentlichen Kinderspielplätzen sowie Grünflächen.

(7) Bei der Errichtung von Betriebsobjekten für die land- und forstwirtschaftliche Nutzung sind für Geschoßflächen, die nicht dem Wohnen dienen, von der errechneten Bauabgabe nur 25 Prozent vorzuschreiben.

(8) Die Vorschreibung der Bauabgabe entfällt:

1. bei der Wiedererrichtung von Gebäuden für dasselbe Ausmaß;
2. bei Nebengebäuden.

<https://www.ris.bka.gv.at/GeltendeFassung.wxe?Abfrage=LrStmk&Gesetzesnummer=20000070>

Projektunterlagen

Donnerstag, 24. Oktober 2019 11:23

- Lageplan, der auszuweisen hat:
  - die Grenzen des Bauplatzes,
  - die auf dem Bauplatz bestehenden und geplanten Bauten mit Nebenanlagen und Freiflächen (Sammelgruben, Kinderspielplätze, Abstellflächen für Kraftfahrzeuge, Stellplätze für Müllbehälter, Anlagen zur Wasser- und Energieversorgung und Abwasserbeseitigung samt Leitungen u.dgl.),
  - die zahlenmäßige Angabe der Abstände der Gebäude von den Nachbargrenzen sowie der Gebäude untereinander,
  - die bestehenden baulichen Anlagen auf den angrenzenden und bis zu 30,0 m von den Bauplatzgrenzen entfernt liegenden Grundstücken mit Angabe der jeweiligen Geschoßanzahl,
  - die Grundstücksnummern,
  - die Grundgrenzen,
  - die Verkehrsflächen,
  - die Nordrichtung,
  - alle am Bauplatz befindlichen sowie die für die Aufschließung des Bauplatzes maßgeblichen Leitungen mit Namen und Anschrift der Leitungsträger,
  - den bekannten höchsten Grundwasserstand und
  - einen Höhenfestpunkt, auf dessen Höhe das gesamte Planwerk zu beziehen ist;

- Grundrisse
  sämtlicher Geschosse mit Angabe der Raumnutzung und der Nutzflächen sowie im Fall des § 92b die Darstellung des Zugangspunktes zum Gebäude;

- Berechnung der Bruttogeschoßflächen
  aller Geschosse in überprüfbarer Form;

- Notwendigen Schnitte,
  insbesondere die Treppenhausschnitte und jene Schnitte, die zur Feststellung der einzuhaltenden Abstände notwendig sind

- alle Ansichten,
  die zur Beurteilung der äußeren Gestaltung der baulichen Anlagen und des Anschlusses an die Nachbargebäude erforderlich sind, sowie Angaben über die Farbgebung

- Darstellung der geplanten Geländeveränderungen
  (ursprüngliches und neues Gelände) in den Schnitten und Ansichten

- Darstellung der Abwasserentsorgungs- und Energieversorgungsanlagen, Düngerstätten u. dgl.

- betreffend Energieeinsparung und Wärmeschutz:

  a. den Energieausweis gemäß § 81;

  b. den Nachweis der Erfüllung der Anforderungen gemäß § 80 in Verbindung mit der Verordnung gemäß § 82, soweit diese Anforderungen im Energieausweis nach lit. a nicht

berücksichtigt sind oder kein Energieausweis zu erstellen ist;

c. gegebenenfalls den durch einen nach den für die Berufsausübung maßgeblichen Vorschriften berechtigten Sachverständigen für das einschlägige Fachgebiet erbrachten Nachweis, dass die Anforderungen gemäß § 80 Abs. 5 berücksichtigt werden;

- baulichen Vorsorge für Heizungsanlagen
  samt Rauchfängen einschließlich der Rauchfanganschlüsse, allfällige Aufzüge, Lüftungs- und Förderleitungen, Klimaanlagen u. dgl.;

- Baubeschreibung - Beschreibung des Bauplatzes und der geplanten baulichen Anlage
  mit Angabe aller für die Bewilligung maßgebenden, aus den Plänen nicht ersichtlichen Umständen, insbesondere auch mit Angaben über den Verwendungszweck der geplanten baulichen Anlagen

Plandarstellung
Lagepläne sind im Maßstab 1:1000, Grundrisse, Schnitte und Ansichten sowie Darstellungen im Sinne des Abs. 1 Z 7 und 9 im Maßstab 1:100, sofern nicht ein größerer oder kleinerer Maßstab für das Vorhaben geeigneter ist, zu verfassen

Die Pläne sind in technisch einwandfreier Form herzustellen. In Plänen für Zu- und Umbauten sind die abzutragenden Bauteile gelb, die neu zu errichtenden Bauteile rot darzustellen.

Die Pläne und die Baubeschreibung sind vom Bauwerber, von den Grundeigentümern oder Bauberechtigten und von den Verfassern der Unterlagen, allfällige weitere Nachweise vom Bauwerber und von den Verfassern der Unterlagen unter Beisetzung ihrer Funktion zu unterfertigen. Als Verfasser der Unterlagen kommen nur dazu gesetzlich Berechtigte in Betracht.

<https://www.ris.bka.gv.at/GeltendeFassung.wxe?Abfrage=LrStmk&Gesetzesnummer=20000070>

Plandarstellung

Mauerwerk und Decken als Stückgut, tragend oder nichttragend

(1) wärmedämmend, zB Ziegel(-decken), Hohlziegel, Leichtbetonsteine — hellrot

(2) ohne besondere Wärmedämmeigenschaft, zB Gipsdielen, Dünnwandsteine, Sichtziegel. — dunkelrot

Mauerwerk und Decken als Schüttgut (geschalt oder mit verlorener Schalung),
z.B. Plattenschalung oder Schalungssteine

(1) wärmedämmend, zB Leichtbeton (-decken), Mantelbeton, Schalungssteine aus Wärmedämmaterial — violett

(2) ohne besondere Wärmedämmeigenschaft, mit vorrangig tragender Funktion, unbewehrt, zB Beton — hellgrün

(3) ohne besondere Wärmedämmeigenschaft, mit vorrangig tragender Funktion, jedoch bewehrt, zB Stahlbeton(-decken). — schwarz oder dunkelgrün

Dämmaterialien

Wärme- und Schalldämmschichten in Wänden und Decken, darstellbar nur bei entsprechendem Maßstab und entsprechender Schichtdicke.

(1) hart (begehbar), zB Schaumglas, Holzwolle-Dämmplatten — orange

(2) weich (nichtbegehbar), zB mineralische Faserdämmstoffe, Polystyrol-Partikelschaumstoff — orange

(3) vor Ort ausgeschäumt — orange

Betonfertigteile

(1) wärmedämmend — violett

(2) ohne besondere Wärmedämmung — schwarz

Holzkonstruktionen im Querschnitt

(1) gehobelt — hellbraun

(2) ungehobelt — hellbraun

SANITÄRGERÄTE UND BEWEGUNGSRAUM

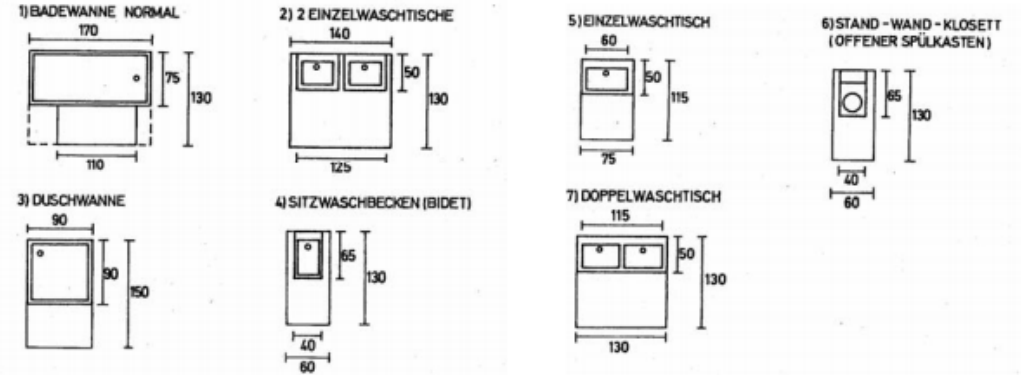

Stahl (Metall)

Sperrschichten (Darstellung eventuell unmaßstäblich)

Rollierung, Steinschüttung

beige

Boden

(1) bestehend (gewachsen) — dunkelbraun

(2) aufgeschüttet — dunkelbraun

Werkstein

(1) Kunststein — hellblau

(2) Naturstein — hellblau

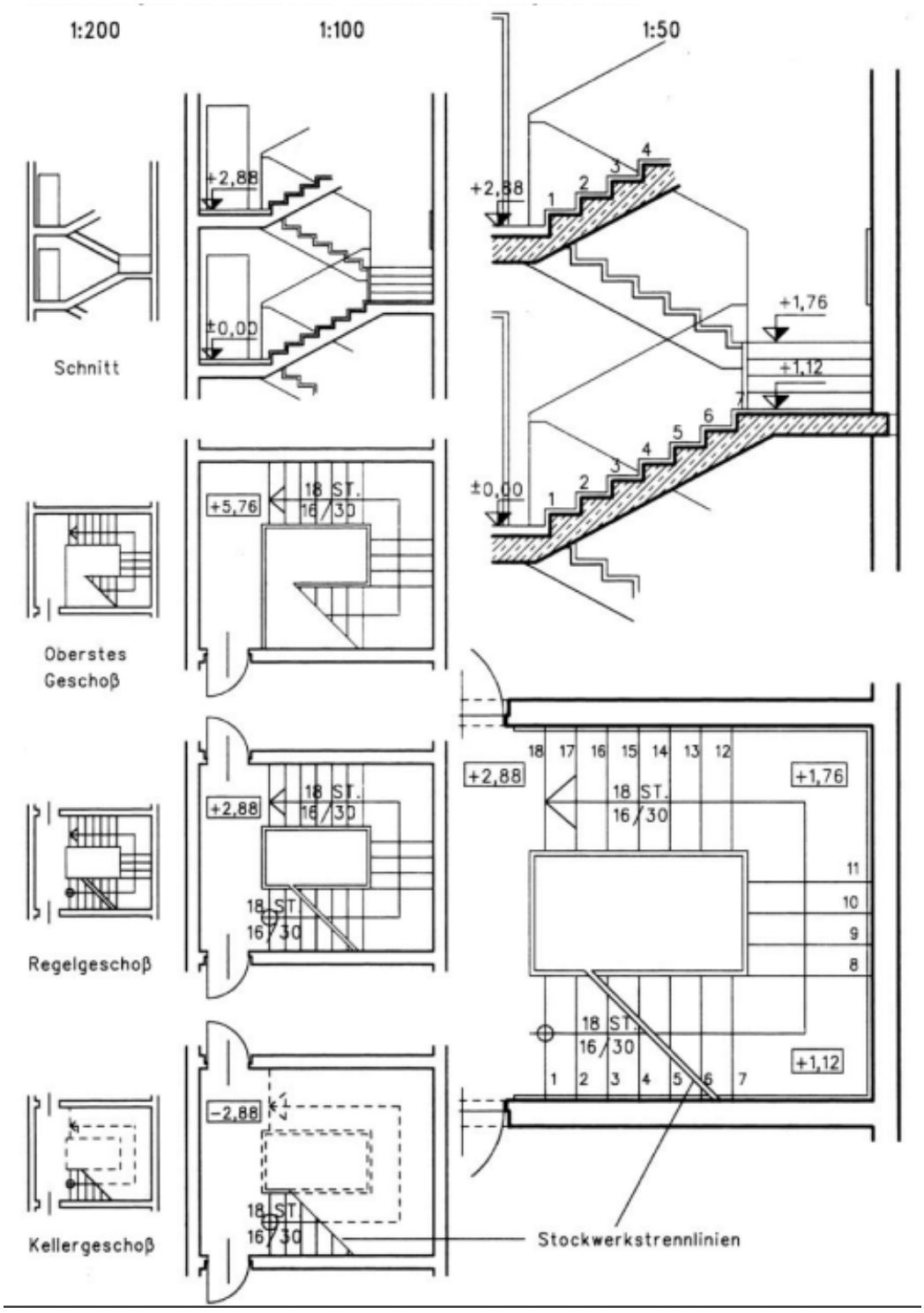
1:200
1:100
1:50
Schnitt
+2,88
±0,00
+1,76
+1,12
Oberstes Geschoß
+5,76
18 ST.
16/30
Regelgeschoß
+2,88
Kellergeschoß
-2,88
Stockwerkstrennlinien

Schematische Darstellung der Öffnungsart von Fenstern in der Ansicht:

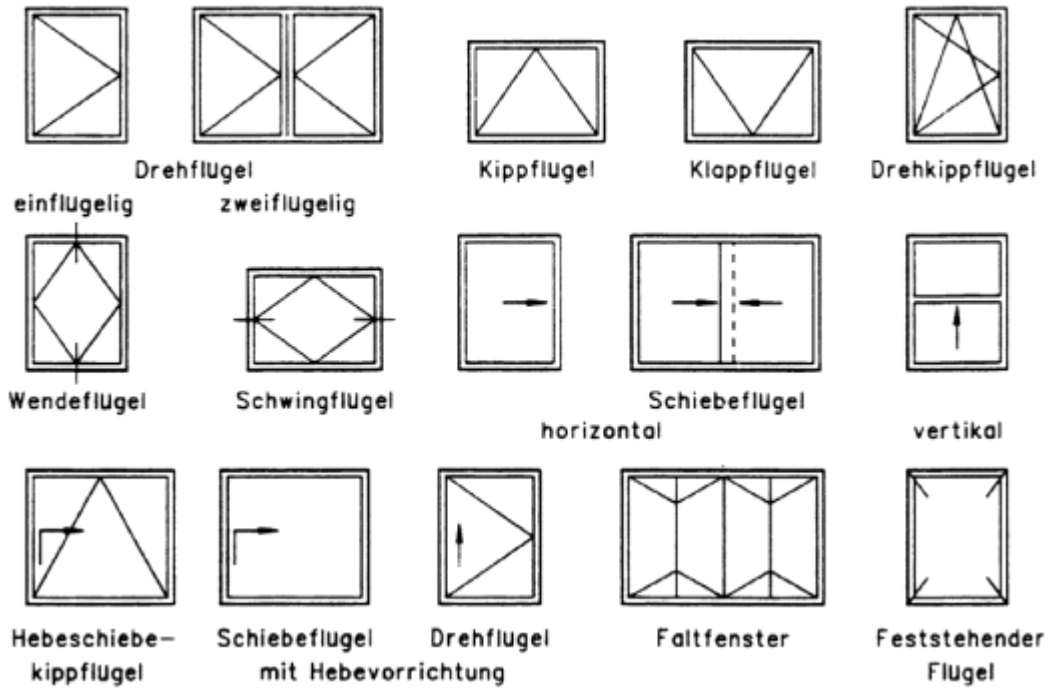

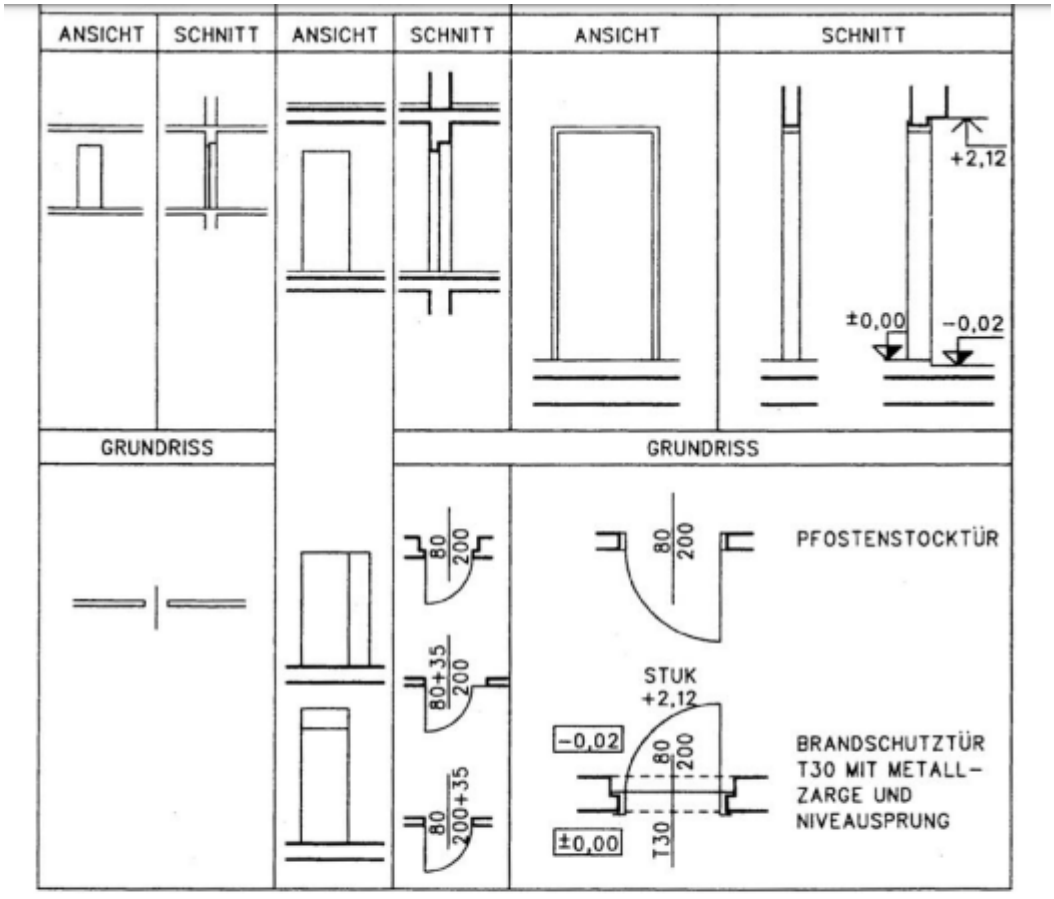

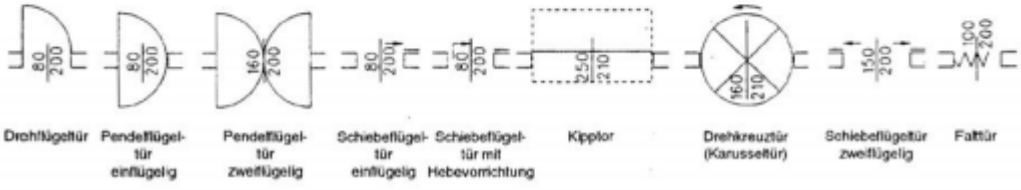

Beispiele für die Darstellung von Fängen:

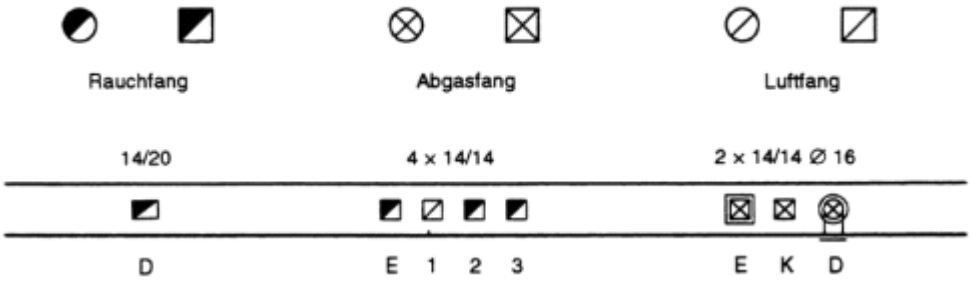

Beispiel Entwässerungsanlage im Einreichplan:

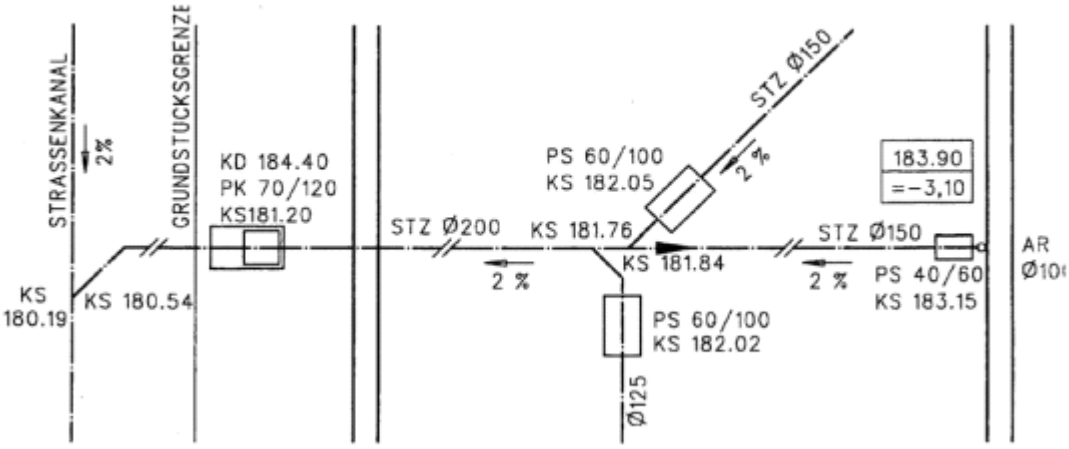

1.) SCHLAFZIMMER:

EINZELBETT 80 / 190
90 / 190
100 / 200

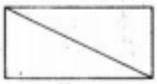

KLEIDERKASTEN 60 / 120

DOPPELBETT 180 / 190
140 / 190
160 / 200
200 / 200

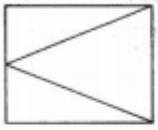

NACHTKÄSTCHEN 40 / 50

KINDERBETT 70 / 150
80 / 160-170

GITTERBETT 85 / 95
55 / 115
60 / 120

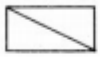

2.) WOHNZIMMER

SOFA 2-FACH
80-100 / 140-180

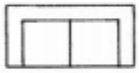

SOFA 1-FACH
80-100/90-110

SOFA 3-FACH
80-100/210-220
HÖHE 70-90 cm
SITZHÖHE 40-45 cm

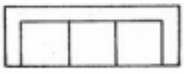

BEISTELLTISCH 60 / 60
70 / 70
70 / 120
HÖHE 40-50 cm



BÜCHERKASTEN
35 - 40 cm TIEF

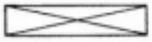

GESCHIRRKASTEN
40 cm TIEF

BÜCHERREGAL MIT UNTERBAU FÜR TV
OBEN 30 cm TIEF
UNTEN 50 - 60 cm TIEF

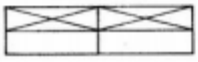

3.) KINDERZIMMER:

SCHREIBTISCH 60 / 120
60 / 150



STOCKBETT 80 / 200

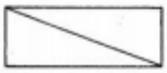

KINDERSESSEL 35 / 35
HÖHE 60 cm
SITZHÖHE 20-30 cm

KINDERTISCH 55 / 75
HÖHE 50 cm

4.) BAD:

WANNE 75 / 170
HÖHE 56 cm

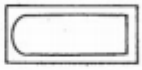

WASCHTISCH 40/60
50/70

BRAUSE 80/80
90/90
70/90

WC

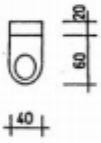

Bestandsplan

Montag, 4. November 2019 22:18

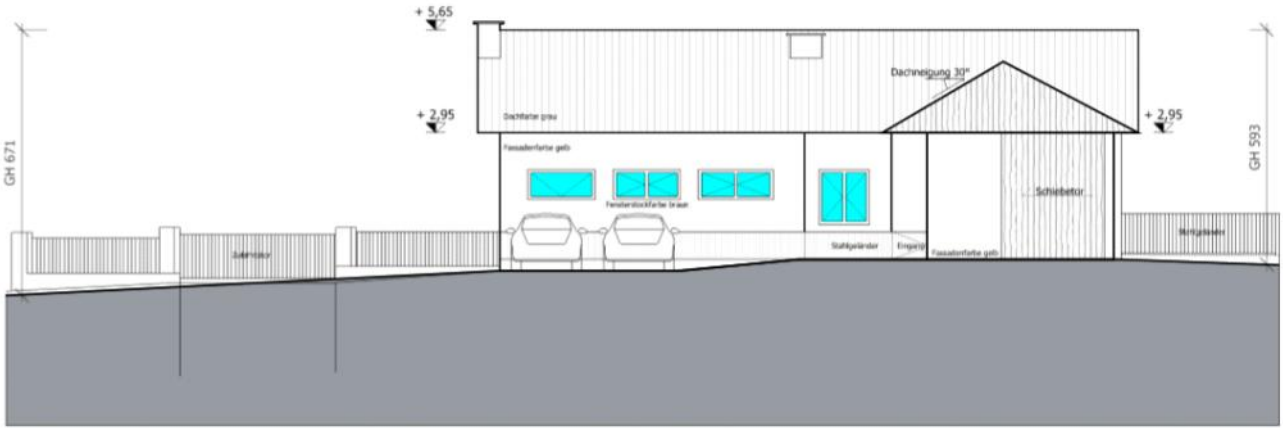

Ansicht Ost

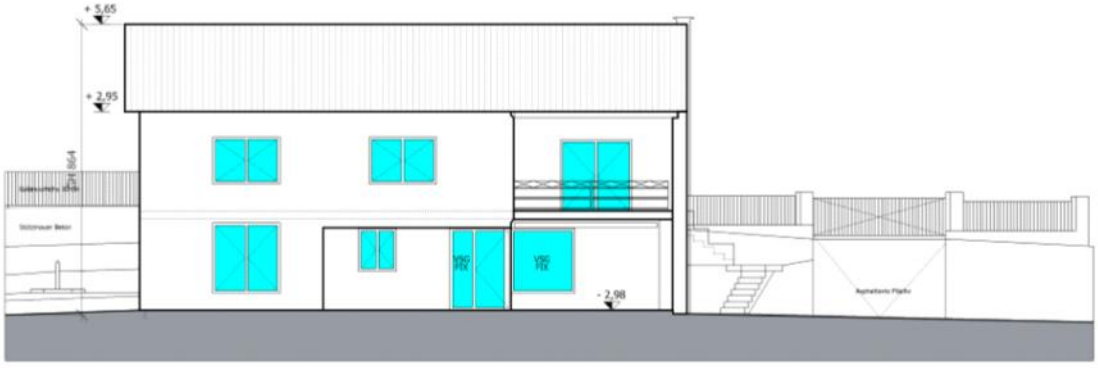

Ansicht West

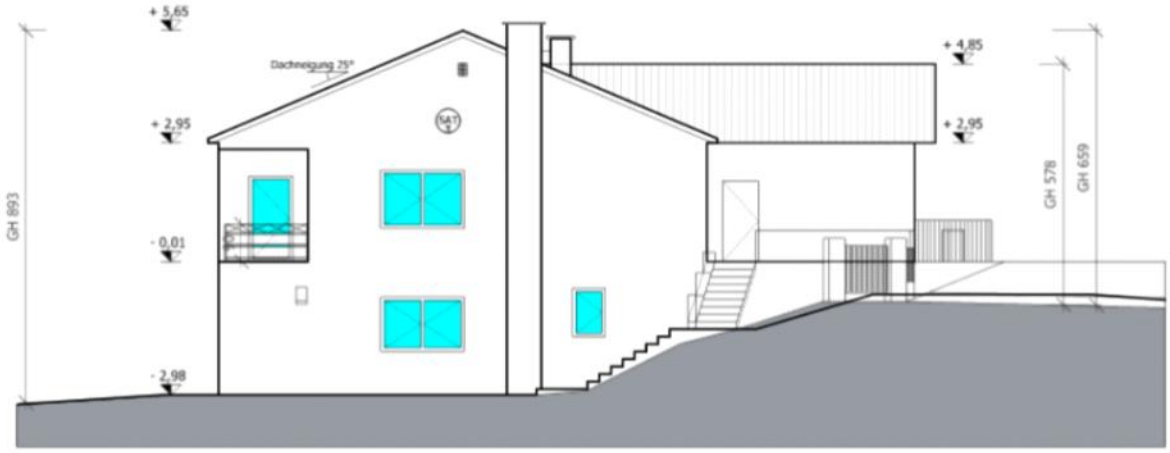

Ansicht Süd

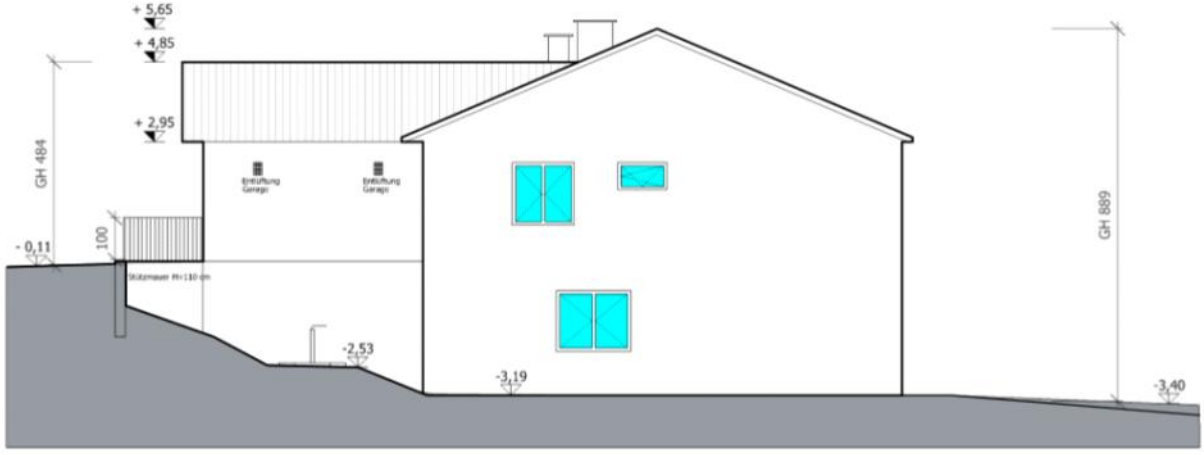

Ansicht Nord

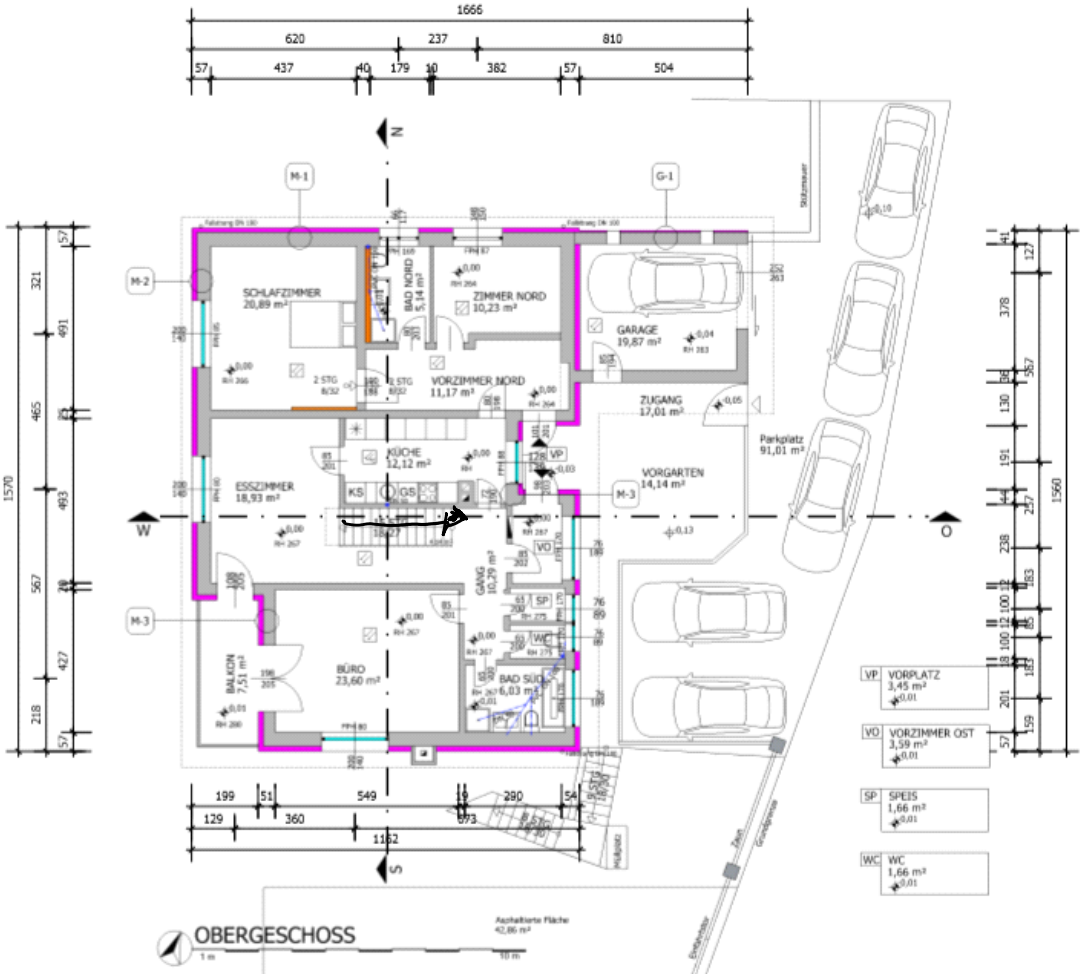
1666
620
237
810
57
437
40
179
10
382
57
504
N
S
W
O
M-1
G-1
M-2
M-3
SCHLAFZIMMER
20,89 m²
BAD NORD
5,14 m²
ZIMMER NORD
10,23 m²
GARAGE
19,87 m²
VORZIMMER NORD
11,17 m²
ZUGANG
17,01 m²
Parkplatz
91,01 m²
KÜCHE
12,12 m²
ESSZIMMER
18,93 m²
VORGARTEN
14,14 m²
GANG
10,29 m²
BALKON
7,51 m²
BÜRO
23,60 m²
BAD SÜD
6,03 m²
VP VORPLATZ
3,45 m²
VO VORZIMMER OST
3,59 m²
SP SPEIS
1,66 m²
WC WC
1,66 m²
1570
1560
199
51
549
19
280
54
129
360
673
1162
OBERGESCHOSS
Aschaltbarte Fläche
42,86 m²

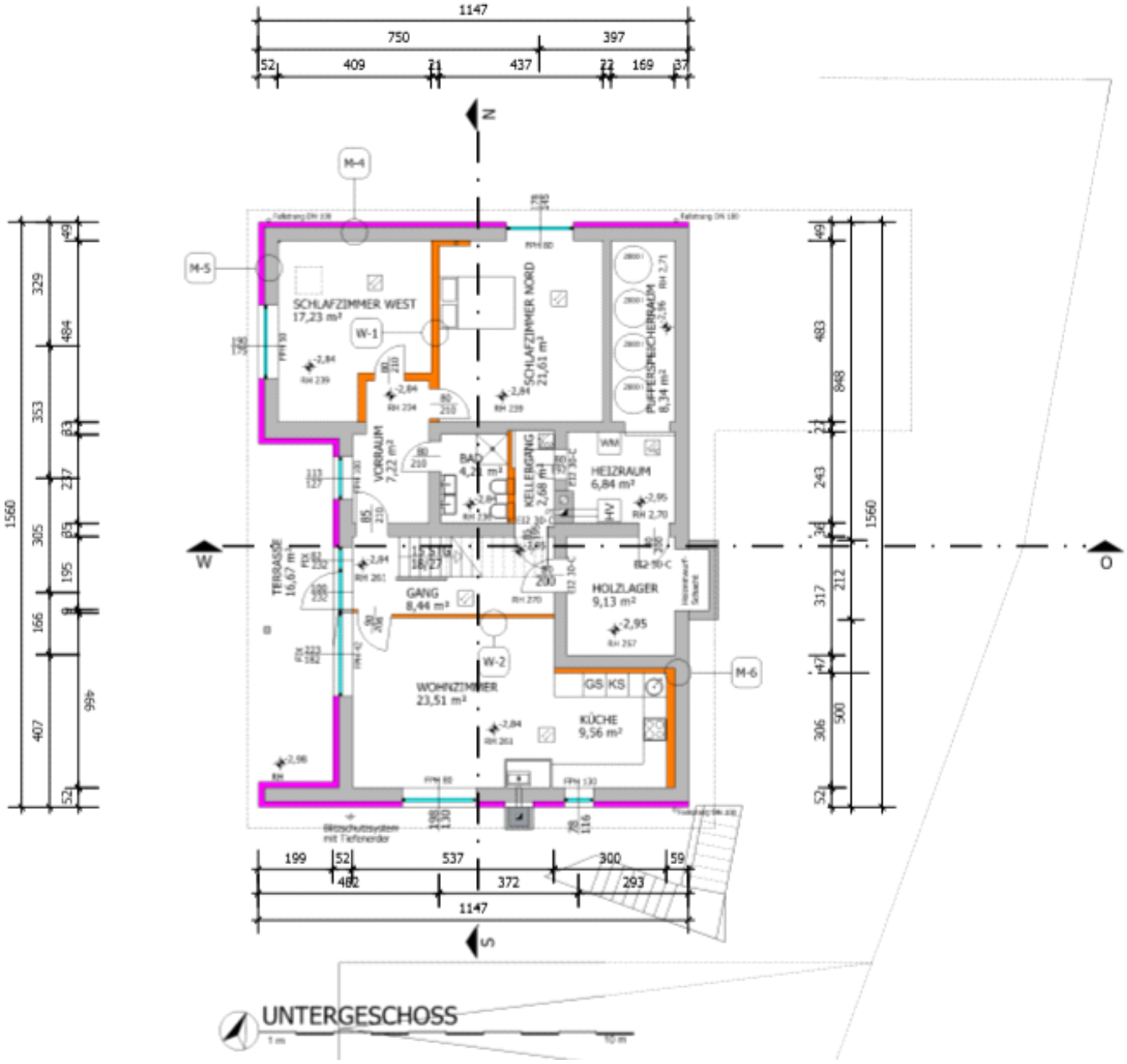
1147
750
397
409
437
169
N
M-4
M-5
SCHLAFZIMMER WEST
17,23 m²
W-1
SCHLAFZIMMER NORD
21,61 m²
PUFFERSPEICHERRAUM
8,34 m²
VORRAUM
7,22 m²
BAD
KELLERGANG
2,68 m²
HEIZRAUM
6,84 m²
WM
HV
TERRASSE
16,67 m²
GANG
8,44 m²
HOLZLAGER
9,13 m²
W-2
WOHNZIMMER
23,51 m²
GS
KS
KÜCHE
9,56 m²
M-6
W
O
S
1560
537
300
372
293
UNTERGESCHOSS

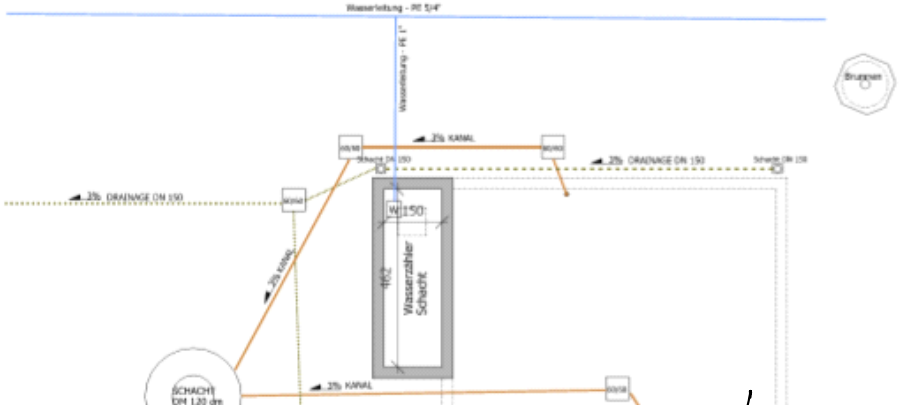
Wasserleitung - PE 5/4"
Wasserleitung - PE 1"
Brunnen
2% KANAL
2% DRAINAGE DN 150
W150
Wasserzähler Schacht
SCHACHT DN 120 cm

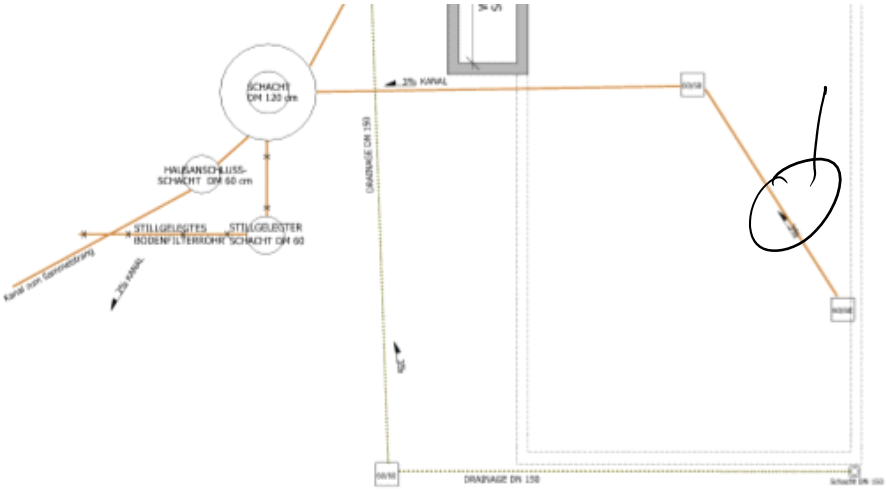

LEITUNGSFÜHRUNGEN

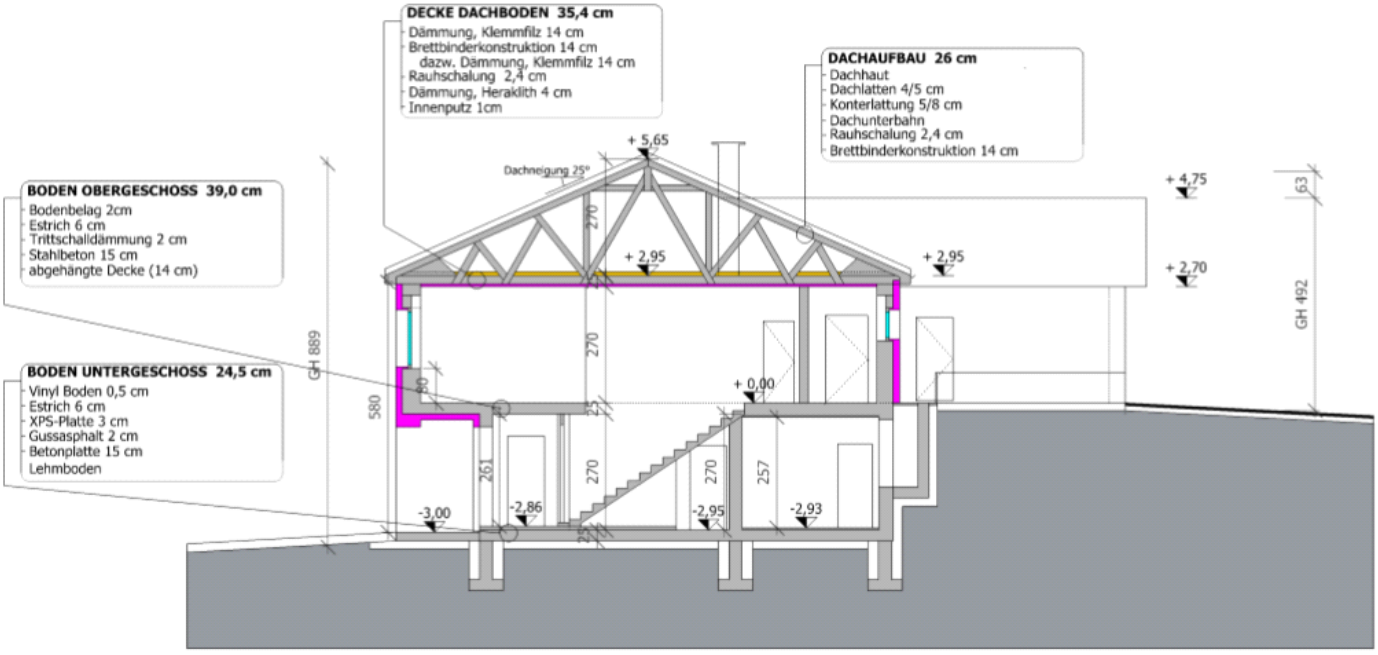

Schnitt WO

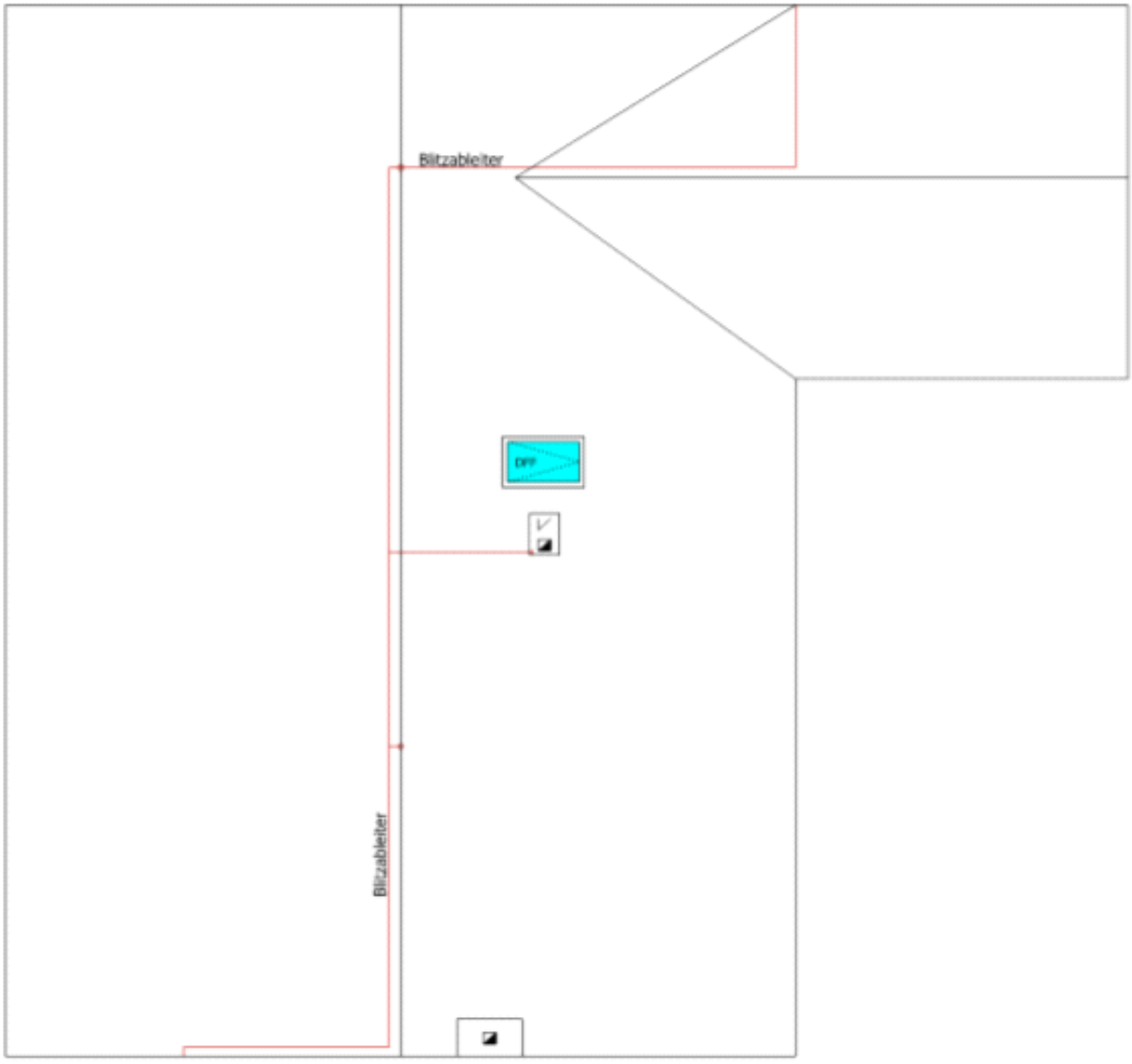

DACHDRAUFSICHT

BRUTTOGESCHOSSFLÄCHEN

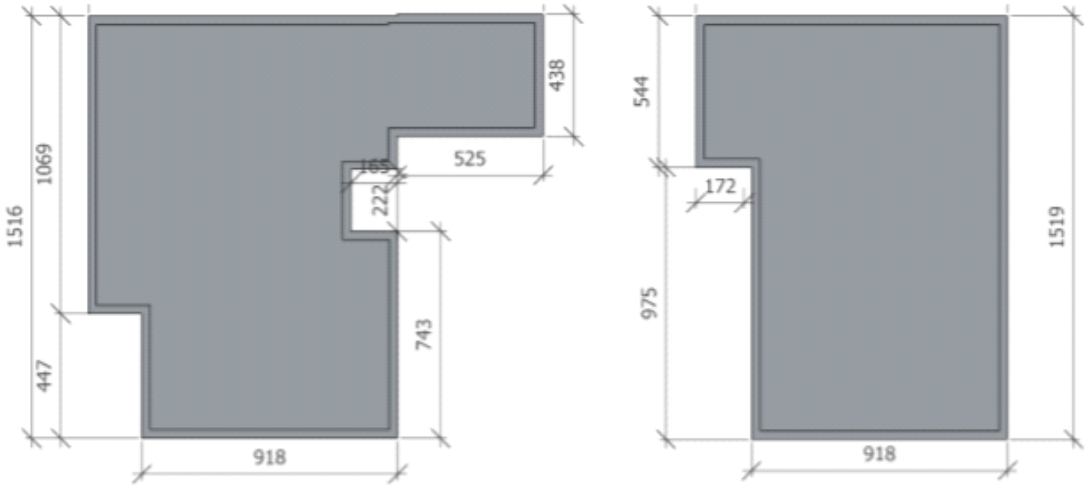

OBERGESCHOSS
178,90 m²

UNTERGESCHOSS
150,25 m²

M=1:200

BESTANDSPLAN

Mühlenweg 36

8046 - Stattegg

KATASTRALGEMEINDE	EINLAGEZAHL	GRUNDSTÜCKSNUMMER
63282 STATTEGG	185	56/4, .148, 55/1

LIEGENSCHAFTSEIGENTÜMER	BAUHERR
Ing. Helmut ZACH Mühlenweg 36 8046 - STATTEGG	-

BAUVORHABEN

Bestandspläne

LAGEPLAN 1:1000

PLANVERFASSER	BAUFÜHRER

PLANINHALT

Allgemein	Ansichten	Grundrisse
Lageplan	Nord Ost	Obergeschoss
Schnitt AA	Nord West	Untergeschoss
Schnitt BB	Süd West	
Dachdraufsicht	Süd Ost	

DATUM	12.10.2019
MASSSTAB	1:100
PLAN NR.	19_M36_BES
VERFASSER	Ebeel